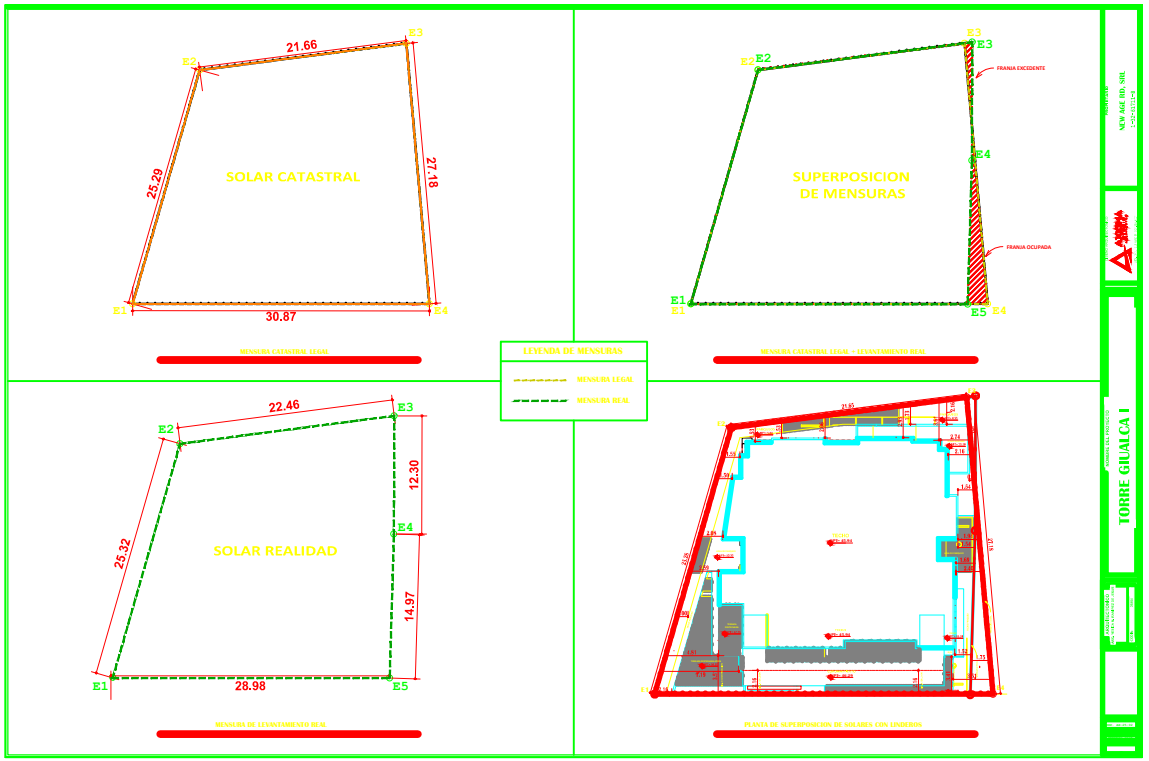

EST.	RUMBO	DIST.
1-	N 21°-28 E	25.28
2-	N 88°-06 E	21.66
3-	S 00°-22 W	27.18
4-	N 84°-34 W	30.87

SOLAR= 669.17 M²

COORDENADAS UTM:

18.479059,
-69.831177

COORDENADAS GPS:

18°28'44.6"N
69°49'52.2"W

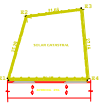

INDICE	
PLANO	NO
INDICE Y PORTADA	01
PLANTA ARQ. Y DIM. SEM SOTANO	02
PLANTA ARQ. Y DIM. NIVEL 1	03
PLANTA ARQ. Y DIM. NIVEL 2	04
PLANTA ARQ. Y DIM. NIVEL 3	05
PLANTA ARQ. Y DIM. NIVEL 4	06
PLANTA ARQ. Y DIM. NIVELES TIPO 5-8	07
PLANTA ARQ. Y DIM. NIVELES TIPO 9-12	08
PLANTA ARQ. Y DIM. NIVEL 13 TIPO PH	09
PLANTA ARQ. Y DIM. NIVEL 14 TIPO ÁTICO A.S.	10
PLANTA ARQ. Y DIM. TECHO	11
ELEVACION FRONTAL Y LATERAL DER.	12
ELEVACION POSTERIOR Y LATERAL IZQ	13
SECCIONES L1 Y T1	14
DETALLE DE ESCALERA	15
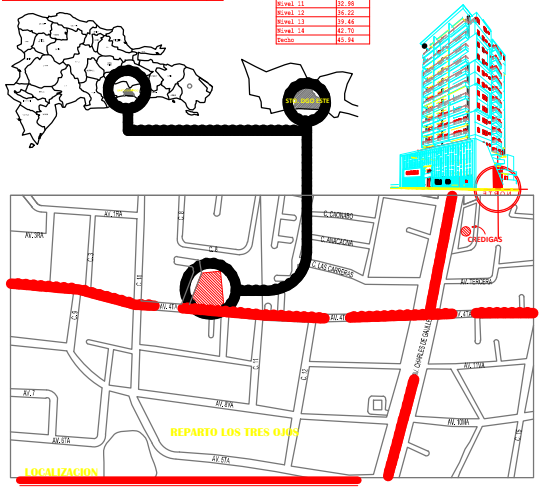
NPT	
NIVEL	NPT
Semi Sotano	-1.40
Nivel 1	0.00
Nivel 2	3.05
Nivel 3	6.60
Nivel 4	10.30
Nivel 5	13.54
Nivel 6	16.78
Nivel 7	20.02
Nivel 8	23.26
Nivel 9	26.50
Nivel 10	29.74
Nivel 11	32.98
Nivel 12	36.22
Nivel 13	39.46
Nivel 14	42.70
Techo	45.94